Untersuchungsraum: Vorarlberger Montafon und Tiroler Gailtal

Bevölkerungsveränderungen zwischen den Jahren 2002 und 2021

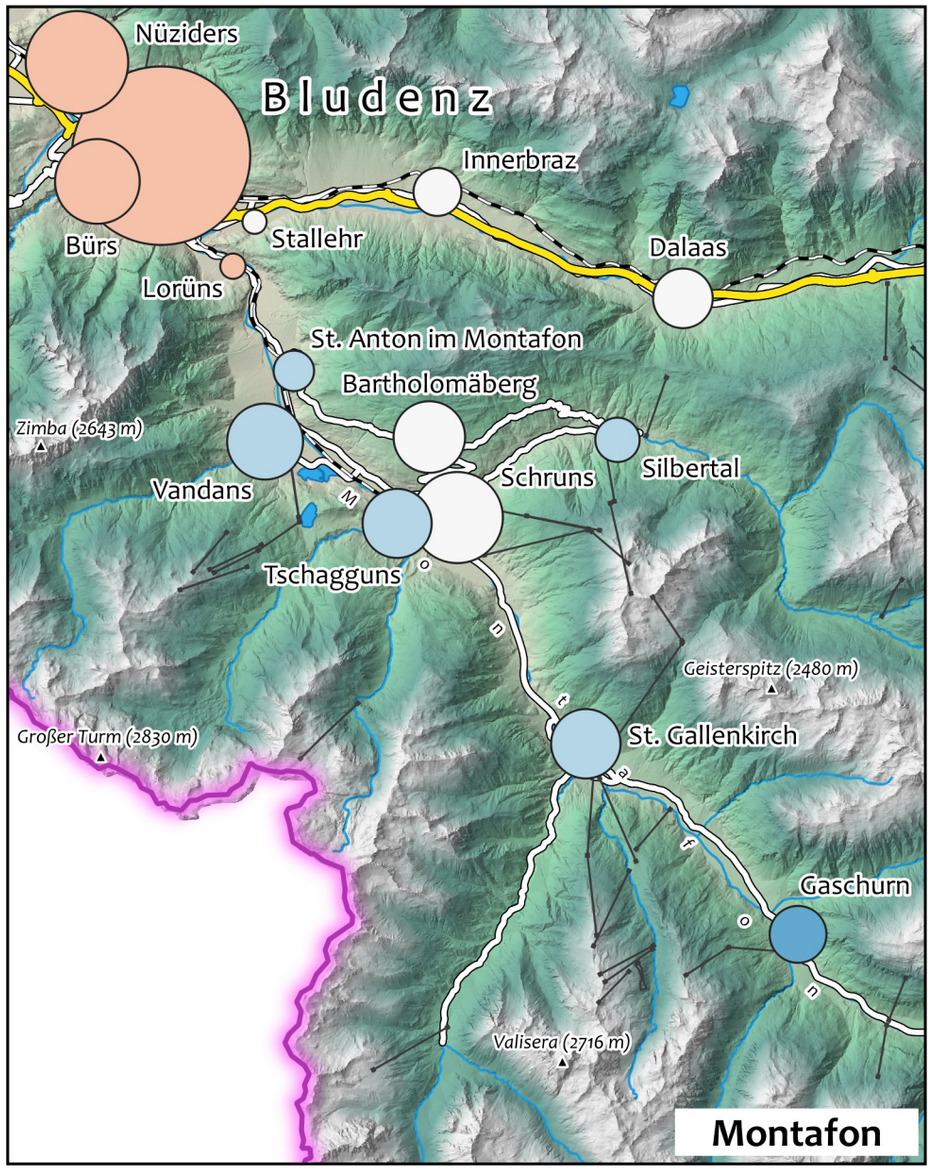

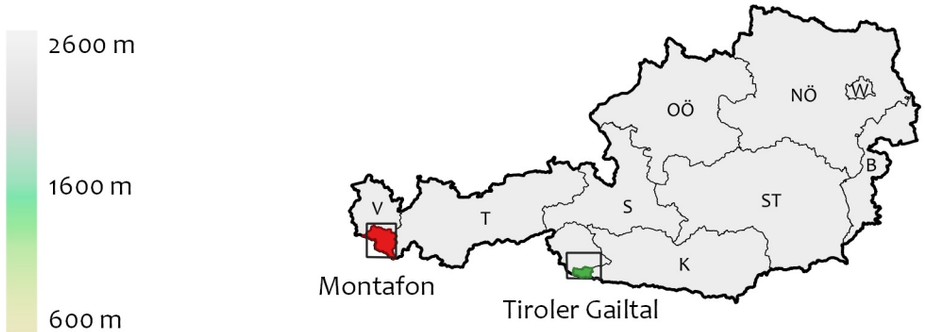

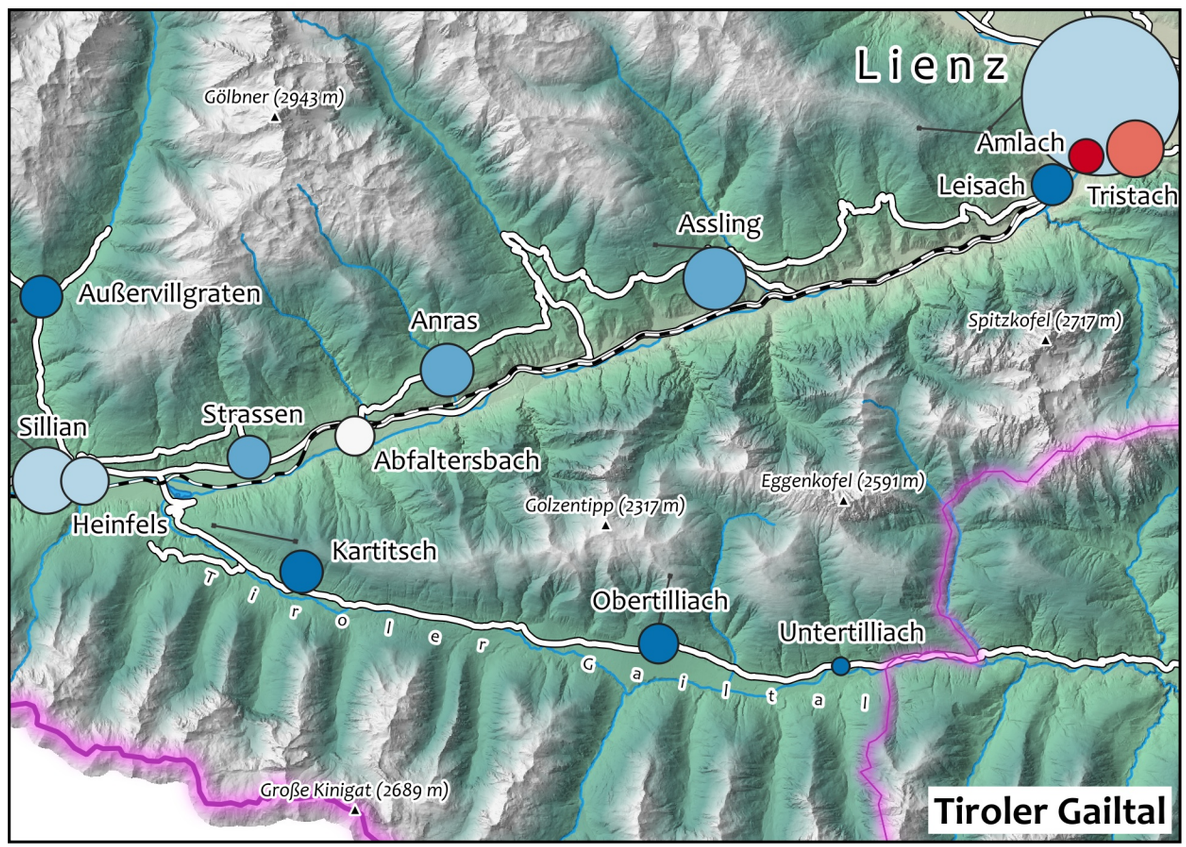

Bevölkerung 2021:

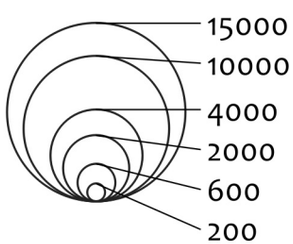

Bevölkerungsveränderung von 2002 auf 2021 (in %):

- -24,0 bis -16,0
- -15,9 bis -8,0
- -7,9 bis 0,0
- 0,1 bis 5,0
- 5,1 bis 12,0
- 12,1 bis 23,0
- 23,1 bis 35,0

- Bahnstrecke
- Bundesstraße, Landesstraße
- Autobahn, Schnellstraße
- Liftanlage (> 1000 m)
- Berggipfel
- Fluss
- See
- Staatsgrenze
- Bundeslandgrenze

N

0 4 8 km

Demographische Daten: Statistik Austria & eigene Berechnungen | Kartengrundlage: www.data.gv.at | Erstellt von: Grüner B. (2021)